A7

JOHANNA MARTINEZ
21-0349
Entrega Final

UNPHU| FAA| EAU
ARQ-446-01 | SEPT-DIC 23
ARQ. SUCRE FERRERAS PÉREZ
ARQ. SAYURI HERRERA

Ubicación

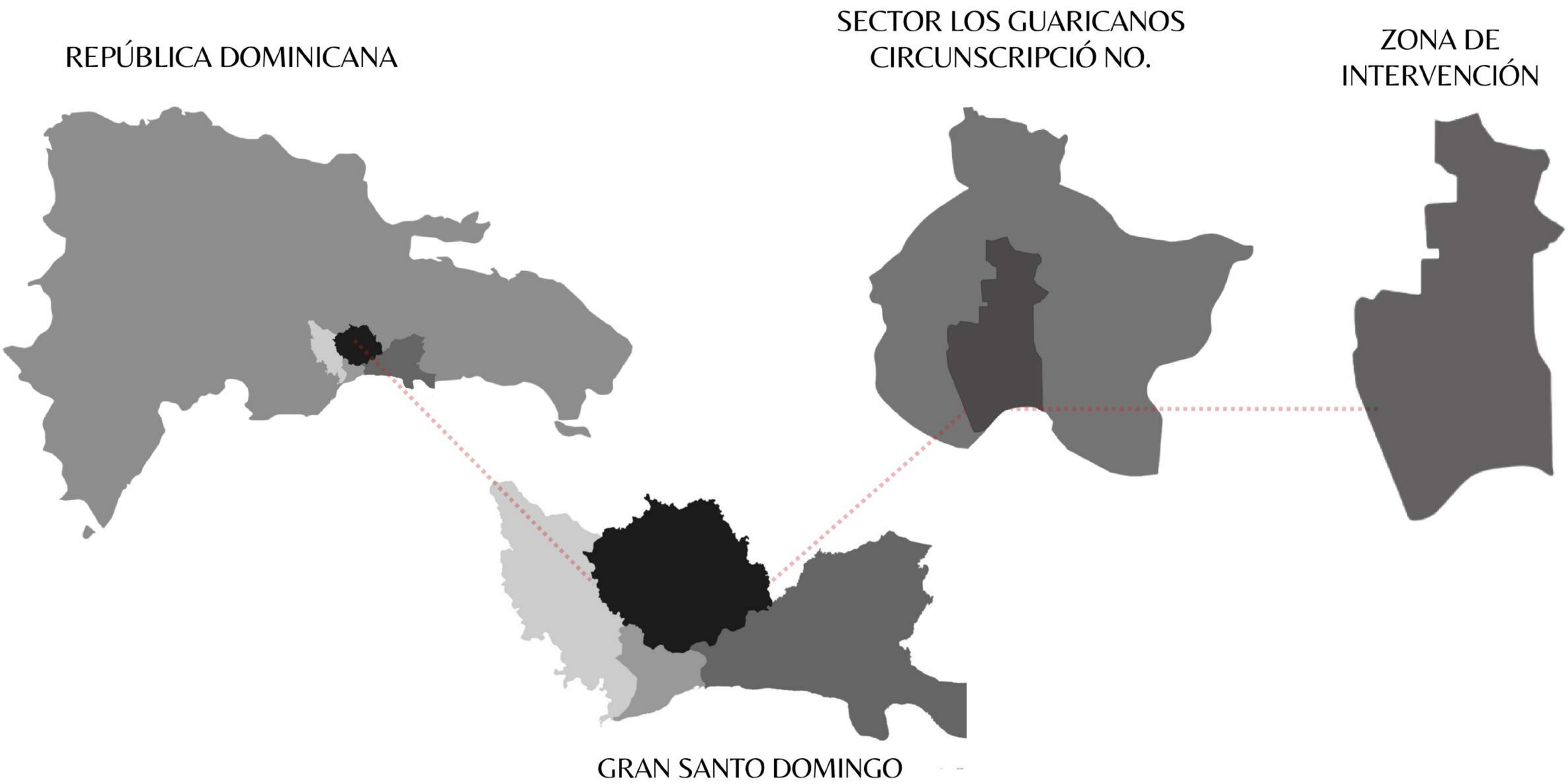
REPÚBLICA DOMINICANA
SECTOR LOS GUARICANOS
CIRCUNSCRIPCIÓ NO.
ZONA DE
INTERVENCIÓN
GRAN SANTO DOMINGO

Ruta Park

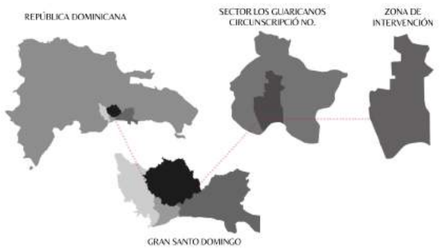

La propuesta seria en un area estratégica para el desarrollo de un Espacio Publico dinámico y multifacético, para que debido a su ubicación favorable permite que sea el centro recreativo por defecto,

con la intención de que sea un ancla para el sector por su accesibilidad y su cercanía con areas residenciales.

Con la Edificaciones existentes Integrara al parque, mediante arborizaciones un acceso que vincule el Interior y el Exterior y atraviesen una un programa recreativo.

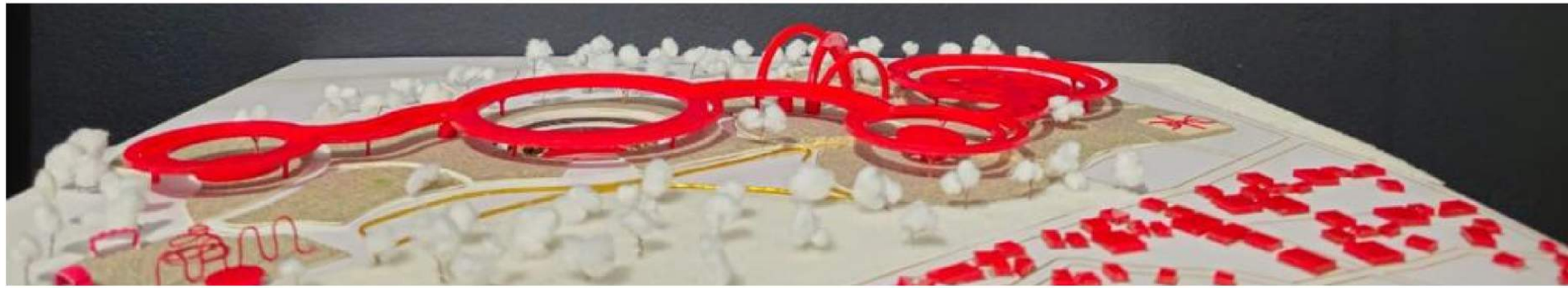





Grafico de Reubicación de viviendas

Memoria Descriptiva: espacios Públicos para Niños en Los Guaricanos, Santo Domingo

Introducción:

El proyecto propone la creación espacios públicos y parques urbanos en Los Guaricanos, Santo Domingo, centrado en brindar a niños y sus padres la oportunidad de apreciar la esencia de su comunidad desde una perspectiva urbanística y lúdica. estos parques serán un entorno seguro, educativos y recreativoS que promoverán la interacción social, el aprendizaje y el juego en un ambiente al aire libre.

Ubicación:

Los parques estaran ubicados en una zonas céntricas de Los Guaricanos, divididos en 3 Bloques A,B,Y C pero que sean de fácil acceso para la comunidad y rodeado de infraestructuras educativas y residenciales. Su diseño se integrará armoniosamente con la arquitectura local y el paisaje circundante.

Características de Los Parques:

1. Áreas Temáticas: El parque contará con áreas temáticas que representan los aspectos más destacados de Los Guaricanos, como la historia local, la naturaleza y la cultura. Estas áreas proporcionarán oportunidades de aprendizaje a través de elementos interactivos y educativos.

2. Juegos : Se incluirán juegos y estructuras de juego adecuadas para diferentes grupos de edad, desde columpios hasta laberintos. Estos elementos fomentarán la creatividad y la actividad física de los niños.

3. Senderos Interpretativos: Senderos a través del parque brindarán a los niños la oportunidad de explorar su entorno y aprender sobre la planificación urbana. Se incorporarán paneles informativos y señalización para explicar aspectos clave de la comunidad.

4. Áreas Verdes: Se establecerán zonas verdes con césped y árboles que ofrecerán espacios para picnic y descanso, fomentando la interacción familiar y comunitaria.

5. Zona de Juegos Acuáticos: Durante los meses más cálidos, se incluirá una zona de juegos acuáticos para que los niños se refresquen y se diviertan.

6. Iluminación Sostenible: La iluminación del parque será eficiente desde el punto de vista energético y estará diseñada para garantizar la seguridad durante la noche.

7. Accesibilidad Universal: El diseño del parque se centrará en la accesibilidad universal, para que todos los niños, independientemente de sus habilidades, puedan disfrutar plenamente del espacio.

Participación Comunitaria: Se llevarán a cabo reuniones de participación comunitaria para involucrar a los residentes de Los Guaricanos en el proceso de diseño y desarrollo del parque, asegurando que refleje las necesidades y deseos de la comunidad. Conclusiones: Este parque urbano en Los Guaricanos será un recurso invaluable para la comunidad, proporcionando un espacio seguro y enriquecedor donde los niños pueden jugar, aprender y conectarse con su entorno. Además, promoverá un mayor sentido de pertenencia y orgullo por su barrio. Su construcción y mantenimiento se llevarán a cabo en colaboración con los residentes locales y las autoridades pertinentes para garantizar su éxito a largo plazo

Graficos Iniciales

Proceso conceptual + Vinculacion Urbana

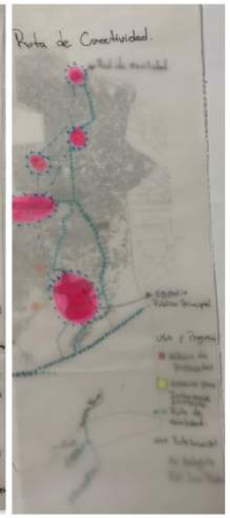

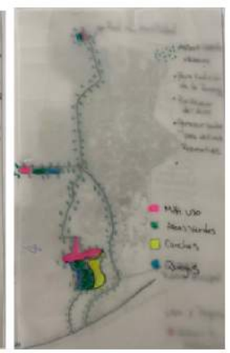

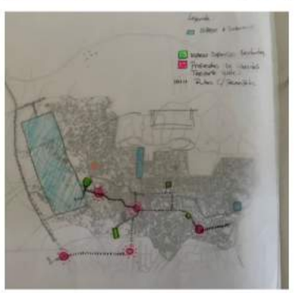

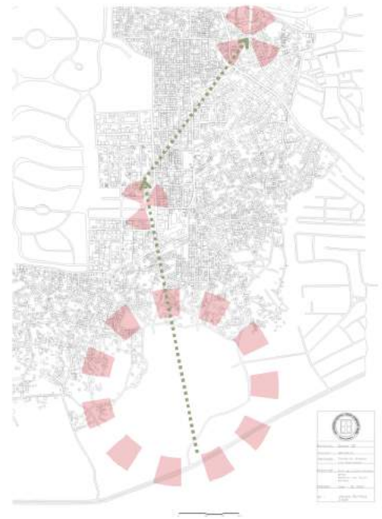

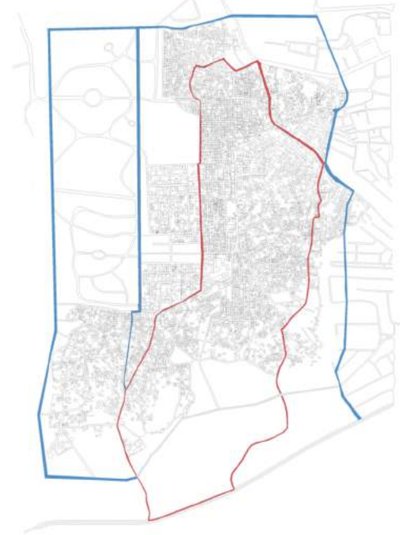

Vias Propuestas
- Existente
- Vias Nuevas propuestas

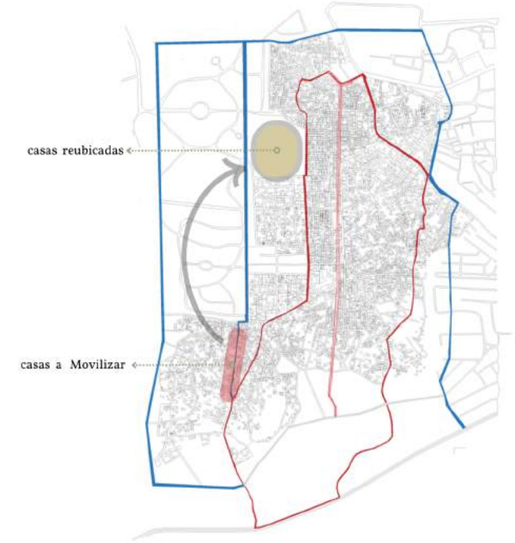

Movilizacion de casa existentes

Reubicacion de viviendas

La Mobilizacion de vivienda es por la nueva calle propuesta

Parque B

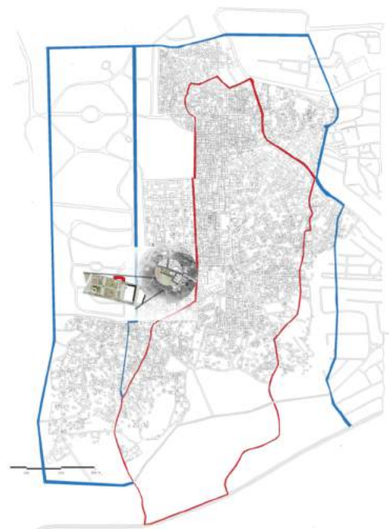

Este parque contara con zona de picnic, un Gym, area para eventos , Juego de Ninos, Juegos de Adolecentes.

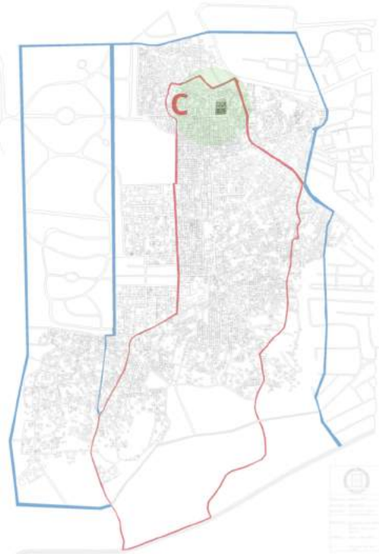

Propuesta de parques

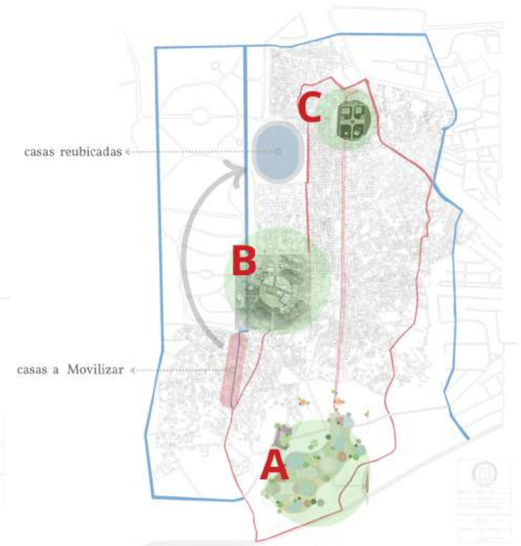

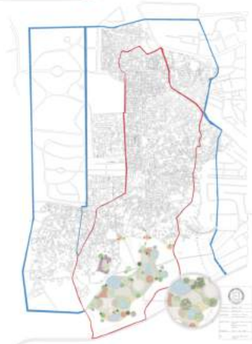

Espacio público orgánico

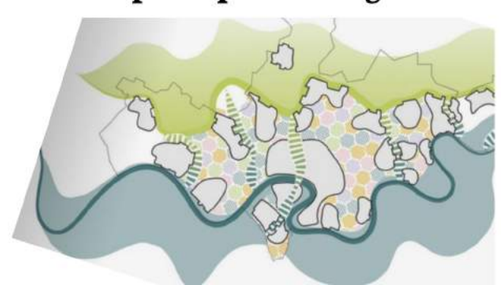

Urbanismo táctico

Espacio Seleccionado para Trabajar a detalle



sección seleccionada

MASTERPLAN DE LLEGADA

CONEXIÓN DE VÍAS EXISTENTES Y PROPUESTAS
MOVILIZACIÓN DE VIVIENDAS

MASTERPLAN DE TECHOS

SECCIONES URBANAS

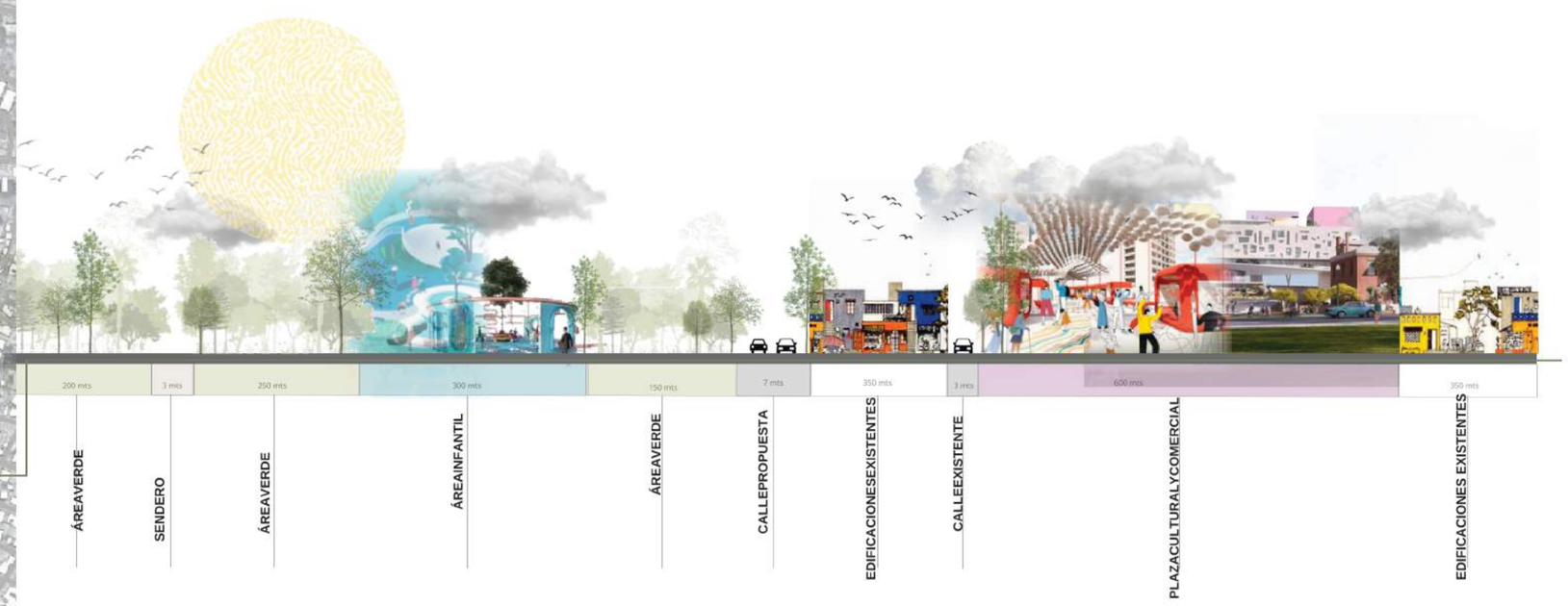

Master de Ciudad

Master de Ciudad
Gran Santo Domingo

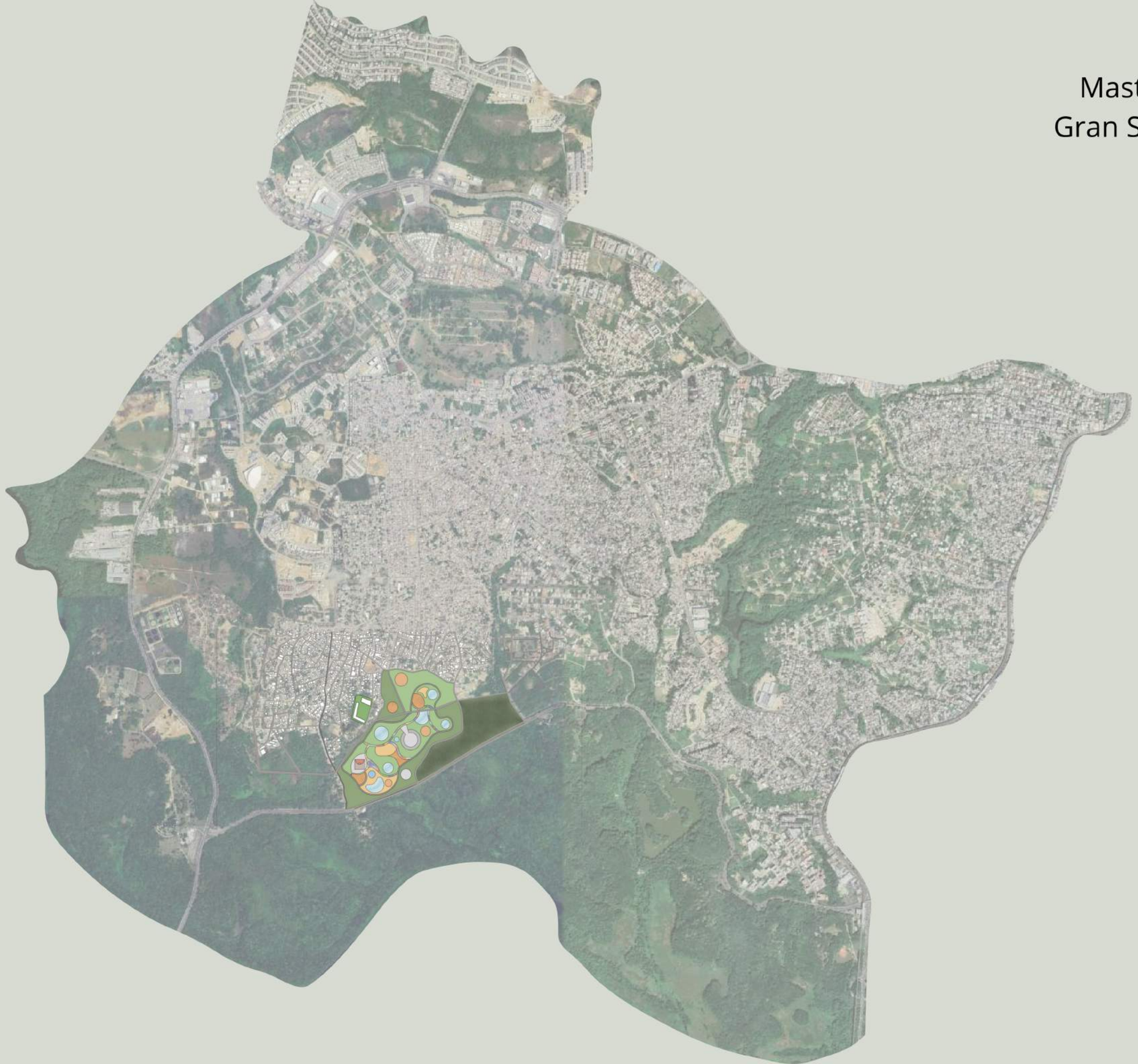

Planta Arquitectonica Nivel 1

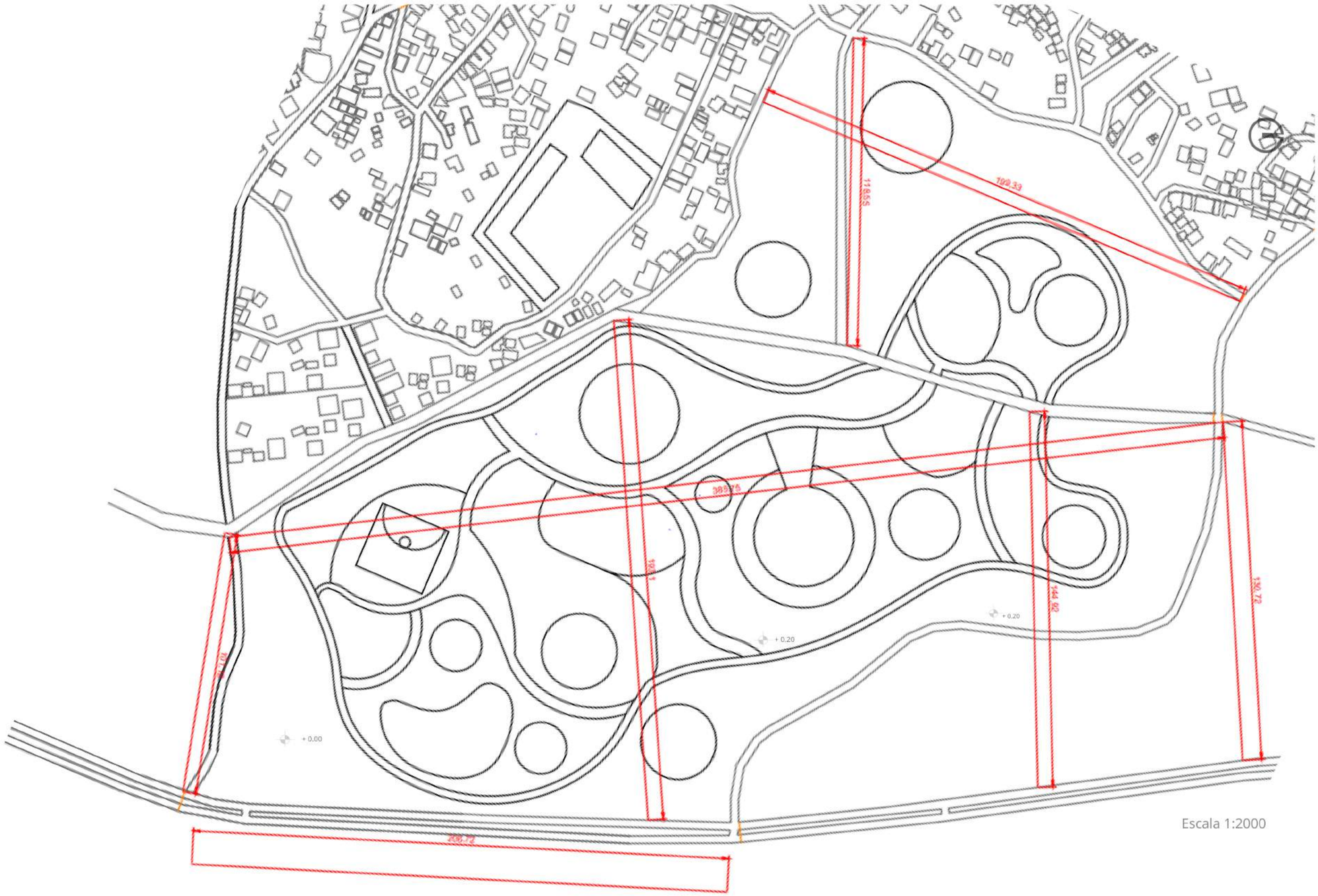

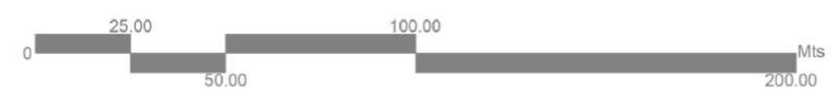

Planta Arq. Techos Conjunto

Escala 1:2000

Planta Techos

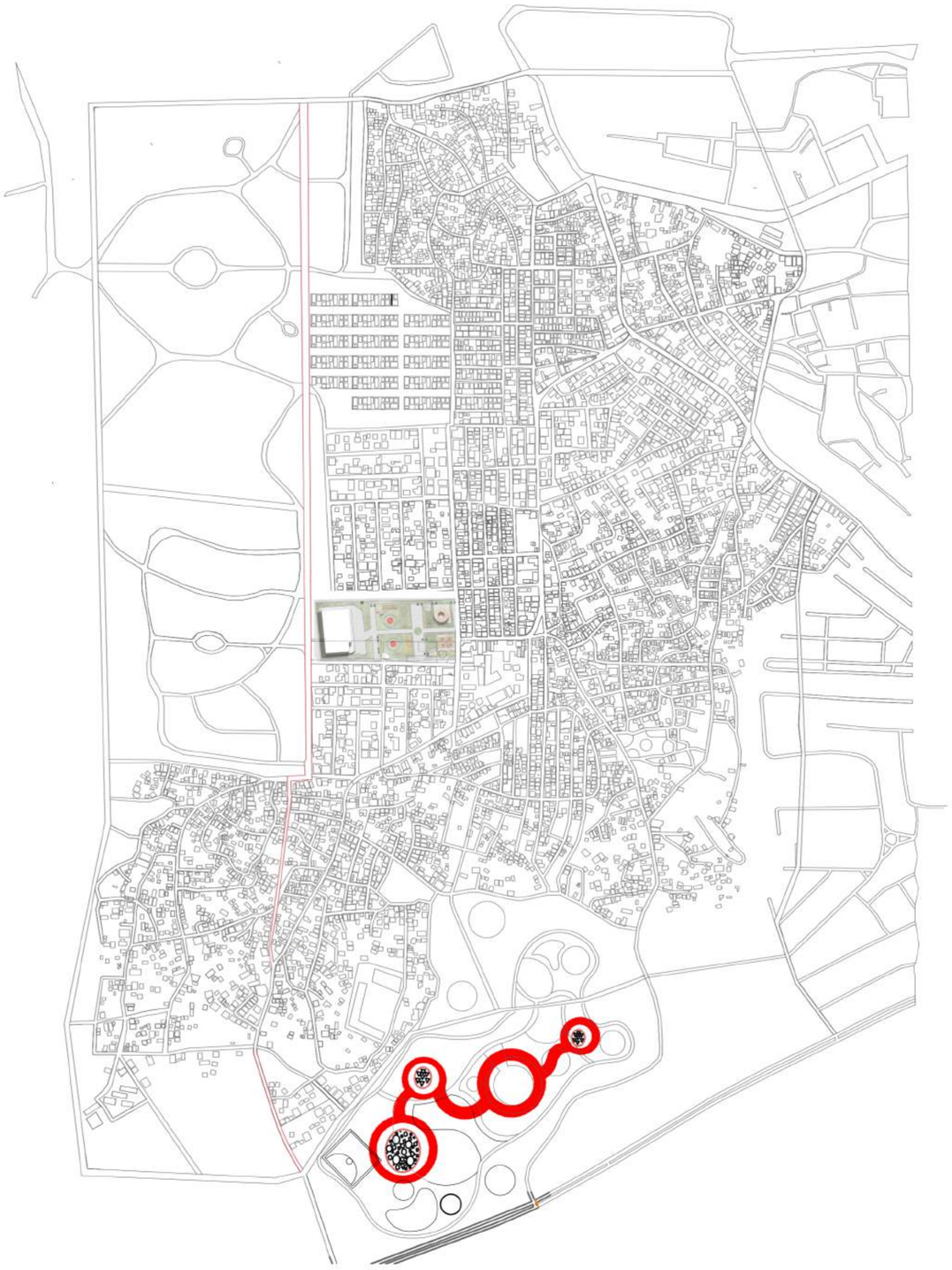

Desarrollo Parque B

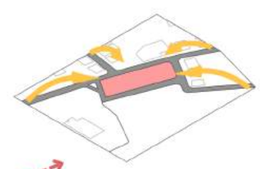

Intervención: Construcción Del Parque. Este no es solo un parque, este Espacio será también un Lugar multiuso en el cual podrán tener varias áreas para toda la familia. Este contará con un salones en los cuales se impartirán clase para niños de bajos recursos Por otro lado contará con un gym para promover el ejercicio en las familias. Así mismo también tendrá un segundo nivel en el cual una zona para celebraciones de eventos, tales como reuniones, cumpleaños, entre otros.

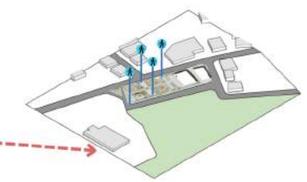

La propuesta pretende generar un parque que reúna exitosamente un entorno agradable para el usuario. por esto contará con áreas de descanso para los adultos y para los niños tendrá diversos Juegos para todas las edades.

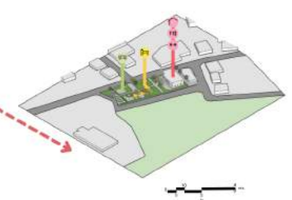

Esta propuesta busca generar un ambiente familiar en el cual reúna exitosamente tanto el área multiuso espacios para clases de manualidades, , un gym y un salon de eventos para el Sector. contará con un área la cual se presta para celebrar cumpleaños de los niños. Para que este sea considerado un lugar en los que se alienta tanto la vida pública como la interacción social. Para Integran colectivamente a persona del Pueblo que puedan utilizar el parque para actividades recreativas y físicas.

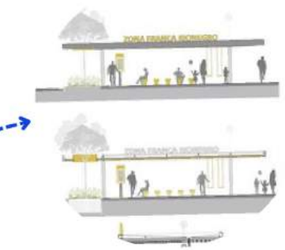

Se propone acondicionar las paradas de Bus

Se propone Intervenir las Aceras agrandándolas y incluyendo mobiliario

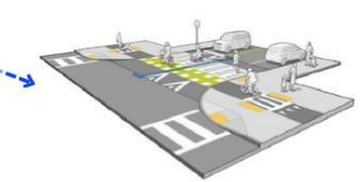

Se propone Intervenir las calles con señalizaciones .

Desarrollo del proyecto:

Lograr un espacio publico de calidad que busque la integración de lo ya existente con la propuesta macro que queremos lograr con el fin de que su percepción no se note desvinculado y aislado del contexto existente, para obtener una aceptación inconsciente de sus habitantes.

Eje de actividades familiares:

- Zona de picnic: area de mesas disponibles en puntos dispersos en el parque para que la familia pueda compartir en un entorno verde.

La Propuesta de Arborización Busca el Objetivo principal de resaltar los Arboles existente en Guaricanos. y proponer espacios con valor ornamental



Los Guaricanos carece de espacios verdes y recreativos y este parque fue diseñado como centro de reunión, Buscando también promover el fortalecimiento de vínculos familiares y redes de organización social, hasta el sentido de pertenencia e identidad con el Pueblo.

Desarrollo del proyecto:

Lograr un espacio publico de calidad que busque la integración de lo ya existente con la propuesta macro que queremos lograr con el fin de que su percepción no se note desvinculado y aislado del contexto existente, para obtener una aceptación inconsciente de sus habitantes.

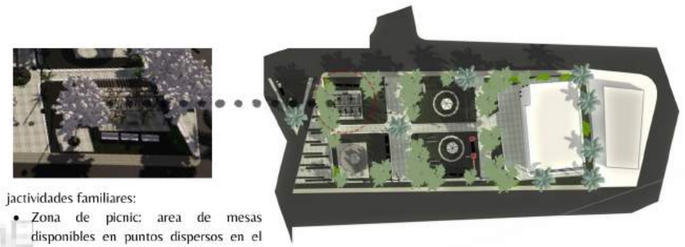

jactividades familiares:

- Zona de picnic: area de mesas disponibles en puntos dispersos en el parque para que la familia pueda compartir en un entorno verde.

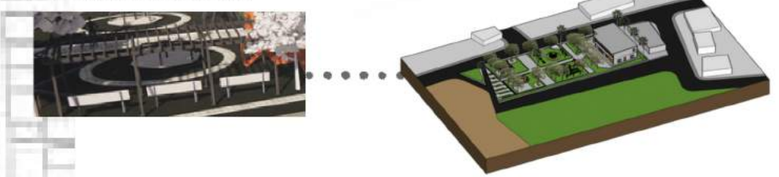

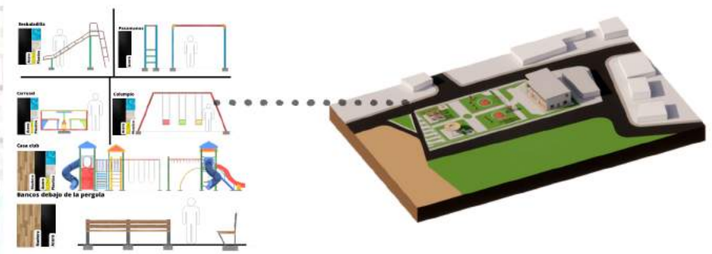

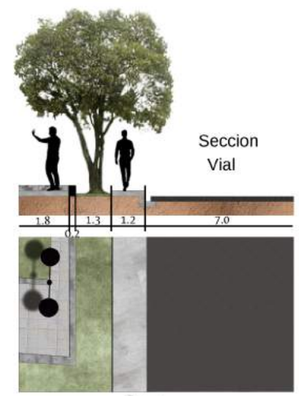

La Propuesta de Arborización Busca el Objetivo principal de resaltar los Arboles existente en Duverge. y proponer espacios con valor ornamental
los Arboles que se seleccionaron fueron Arbol de cedro, Arbol de ocobo, Arbol de saman y Arbol de ceiba. estos son arboles de diferente escala para que el parque mantenga la belleza a lo largo del ano

Parque C
Sección

Maqueta Final